Reversión de tableros de control del ministerio de economía referidos a la actividad en Upstream en argentina

Categoría: Data-Drill / Data Management mediante Power-BI

Fecha: Marzo de 2026

Autor: Diego Angeloni

Introducción

A continuación, se muestran tableros de control referidos a perforación, estimulación y producción de pozos de hidrocarburos a nivel nacional.

Cabe destacar que la funcionalidad de un Dashboards vive dentro de un entorno como Excel o Power-BI donde el usuario puede segmentar la información que desea ver, por lo que en las siguientes páginas solo se presentan imágenes de estos con un filtrado mínimo de información.

Los datos utilizados fueron sacados de la página del ministerio de economía de la nación que regularmente actualiza sus planillas con información referida a cada cuenca, empresa, yacimiento y operación dentro del país.

ARGENTINA UPSTREAM DASHBOARDS

PERFORACIÓN

SELECCIÓN DE PÁGINA

- Historial de perforación
- Áreas y Empresas
- Objetivo de pozos

HISTORIAL DE PERFORACIÓN

Distribución de pozos por provincia y tipo en los últimos años

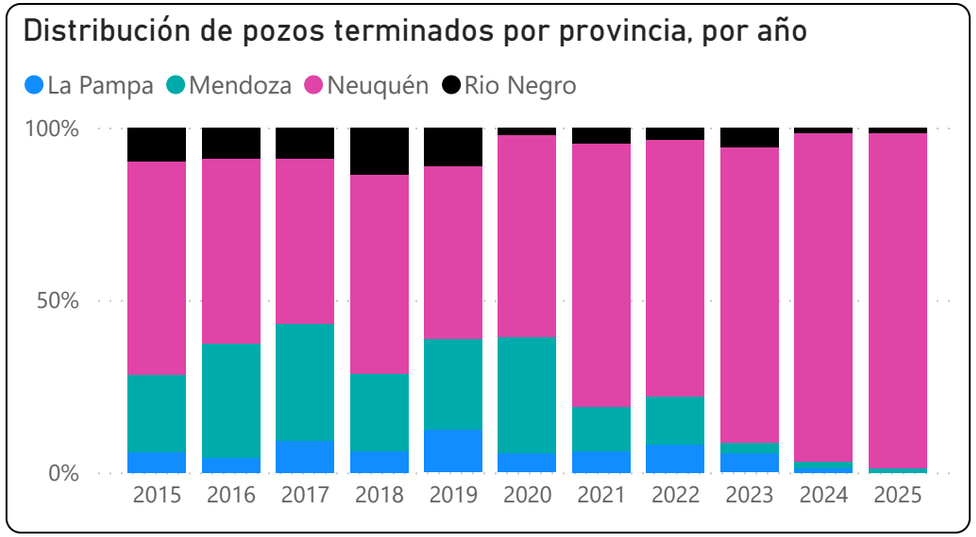

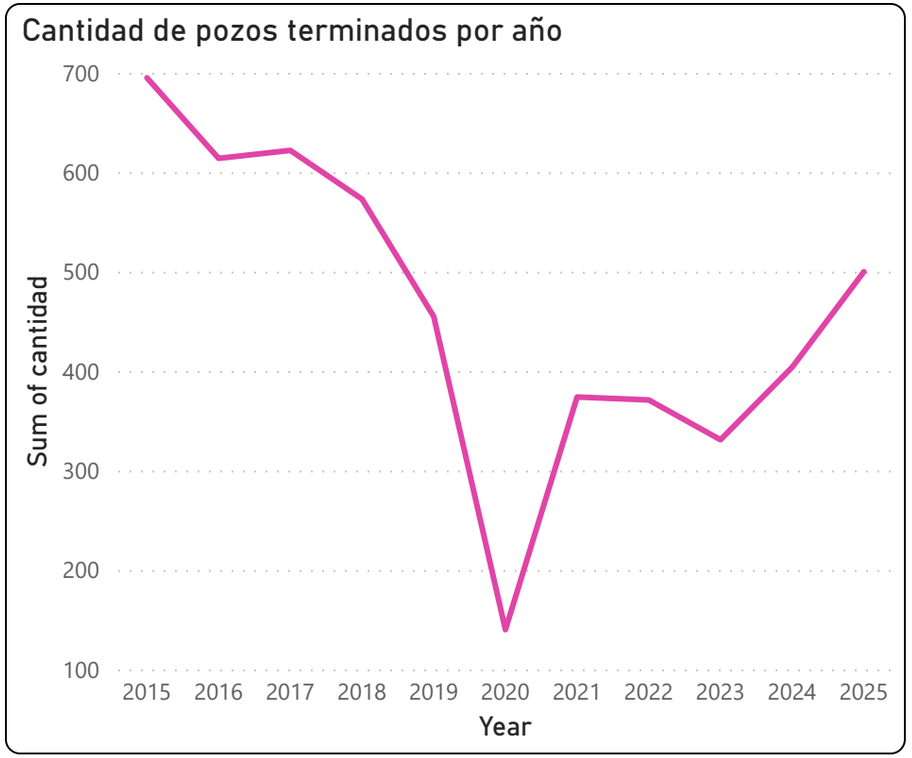

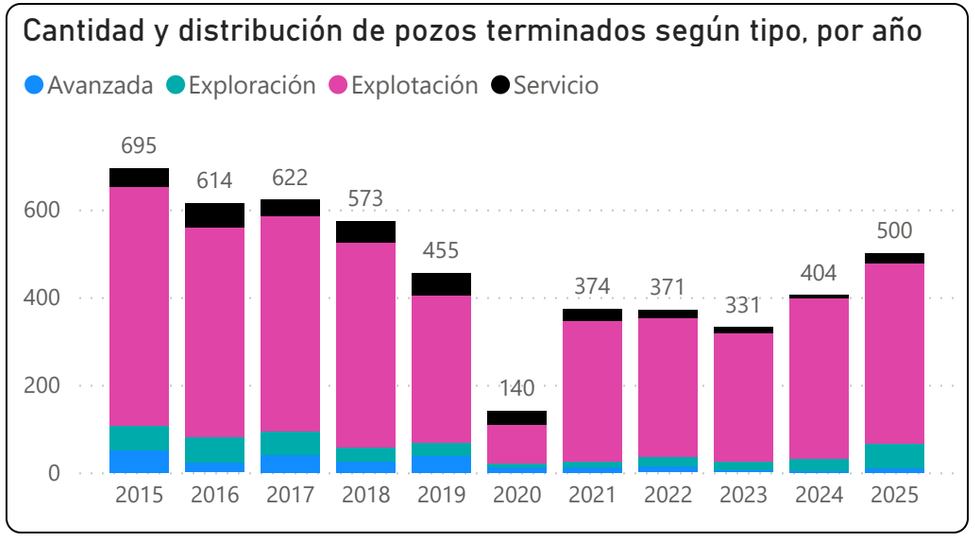

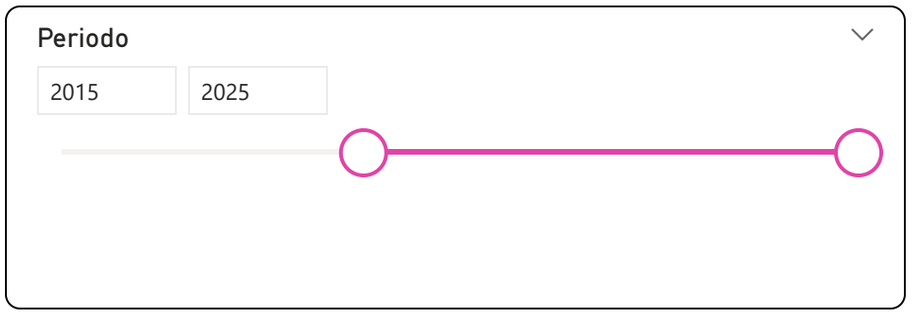

Diego Angeloni - Marzo 2026

ARGENTINA UPSTREAM DASHBOARDS

PERFORACIÓN

SELECCIÓN DE PÁGINA

- Historial de perforación
- Áreas y Empresas
- Objetivo de pozos

ÁREAS Y EMPRESAS

Preponderancia de las principales áreas y sus respectivas operadoras

Buscar área:

All

Áreas

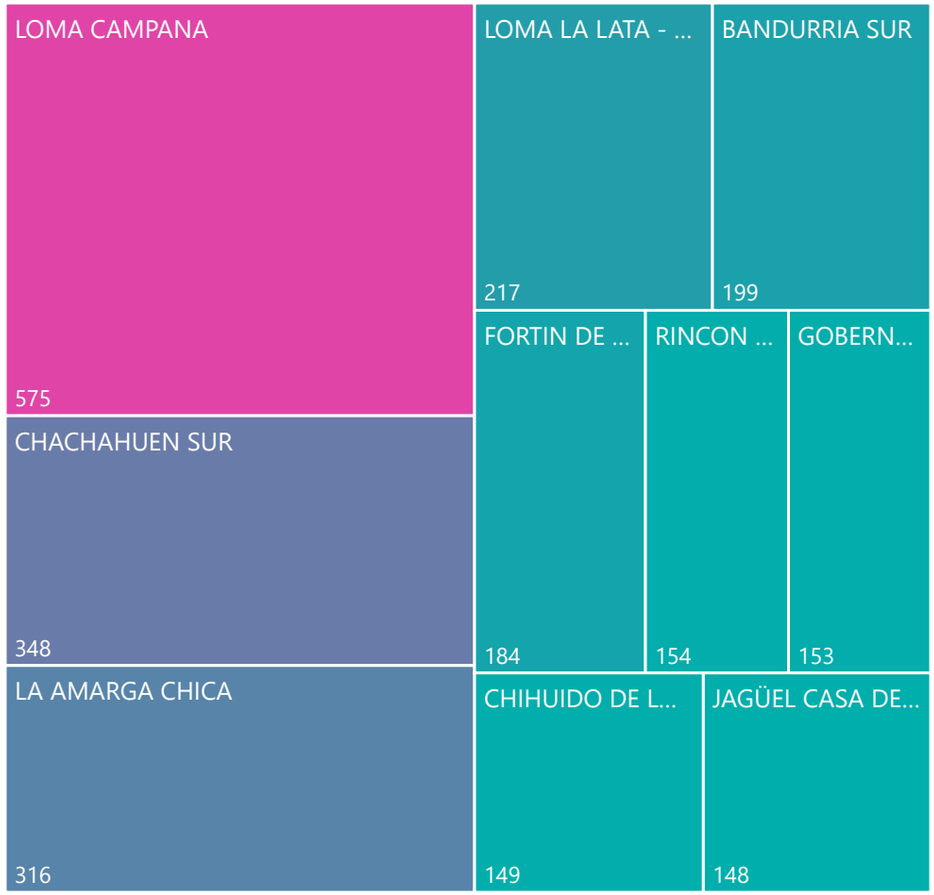

Buscar empresa:

All

Empresas

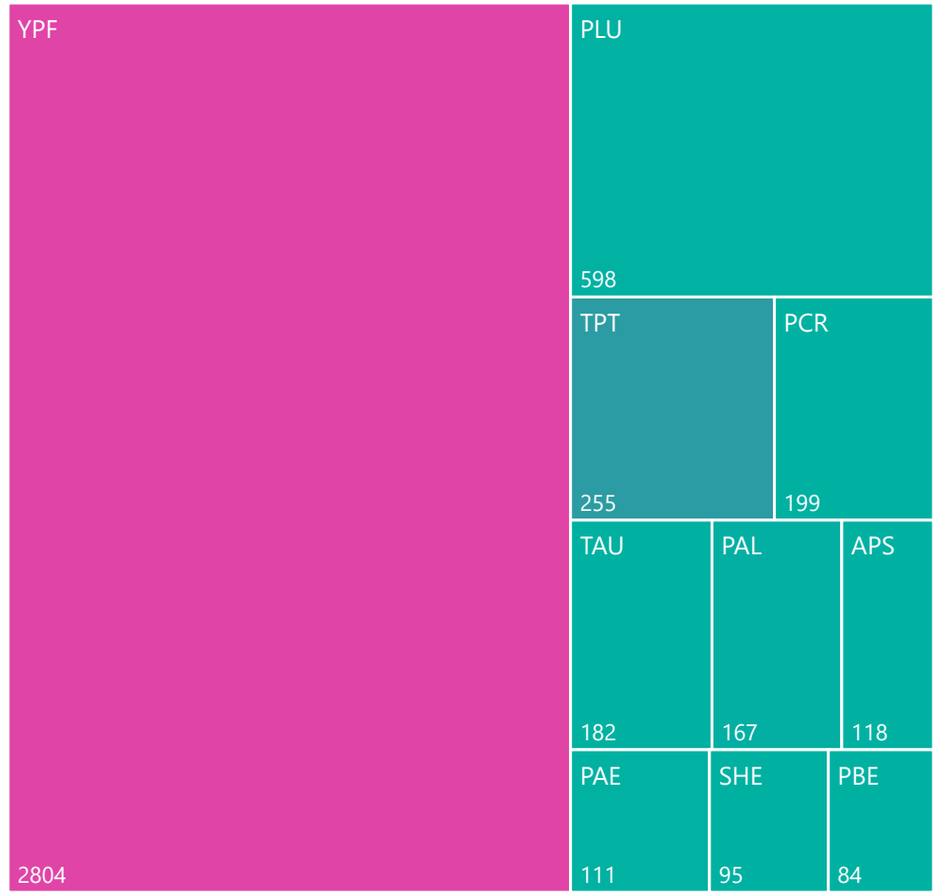

Diego Angeloni - Marzo 2026

ARGENTINA
UPSTREAM
DASHBOARDS

PERFORACIÓN

SELECCIÓN DE PÁGINA

- Historial de perforación
- Áreas y Empresas
- Objetivo de pozos

OBJETIVO DE POZOS

Distribución de pozos terminados por área y principal fluido de extracción

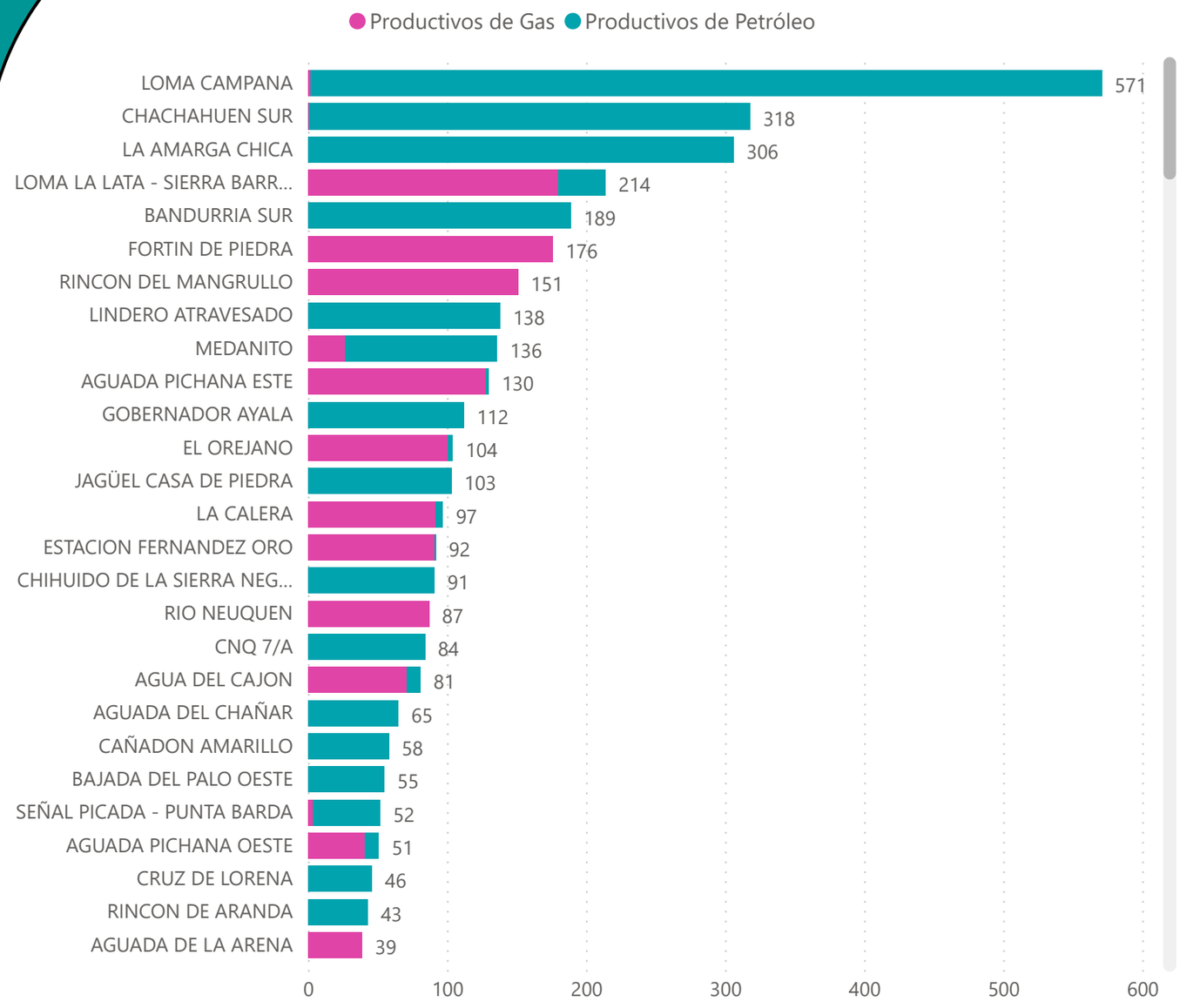

Tipo de pozo:

Productivos de Gas | Productivos de Petróleo

Buscar empresa:

All

Buscar área:

All

Periodo:

2015 | 2025

Diego Angeloni - Marzo 2026

ARGENTINA UPSTREAM DASHBOARDS

FRACKING

SELECCIÓN DE PÁGINA

- ACTIVIDAD
- INSUMOS
- PARÁMETROS

ACTIVIDAD

Empresas y áreas con mayor preponderancia

Cantidad de fracturas por año

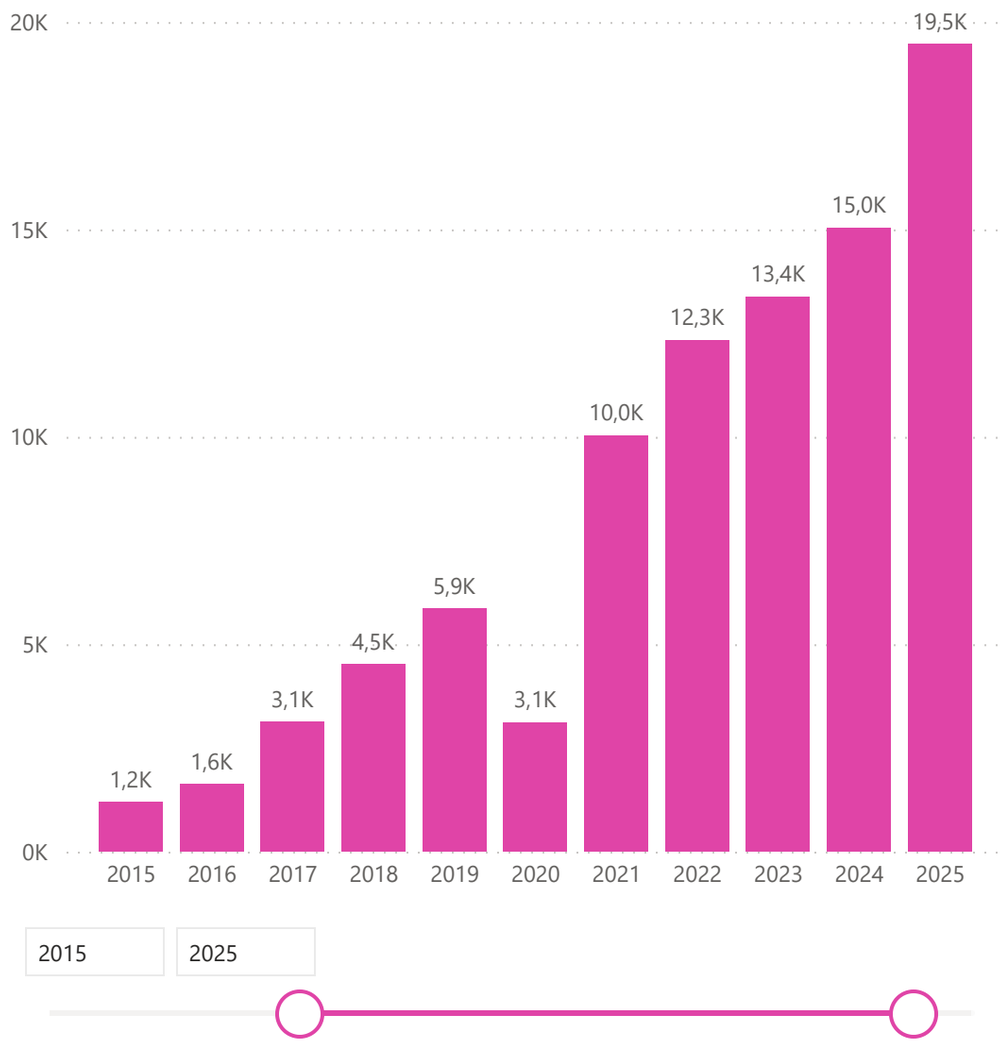

Áreas

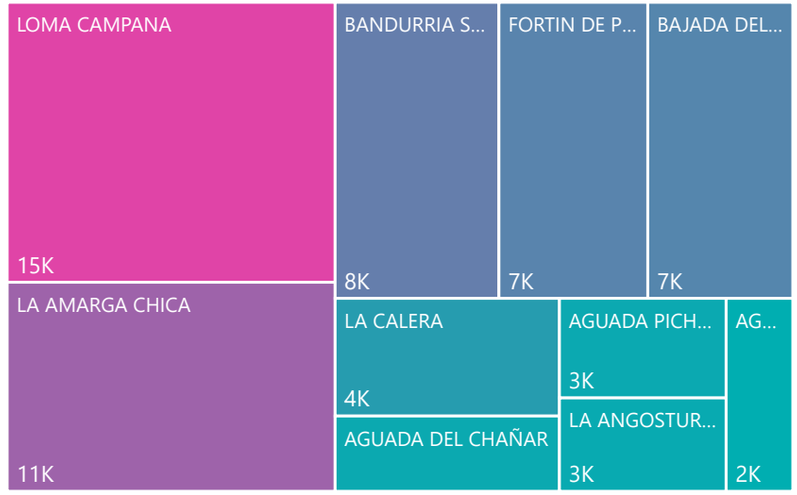

Empresa

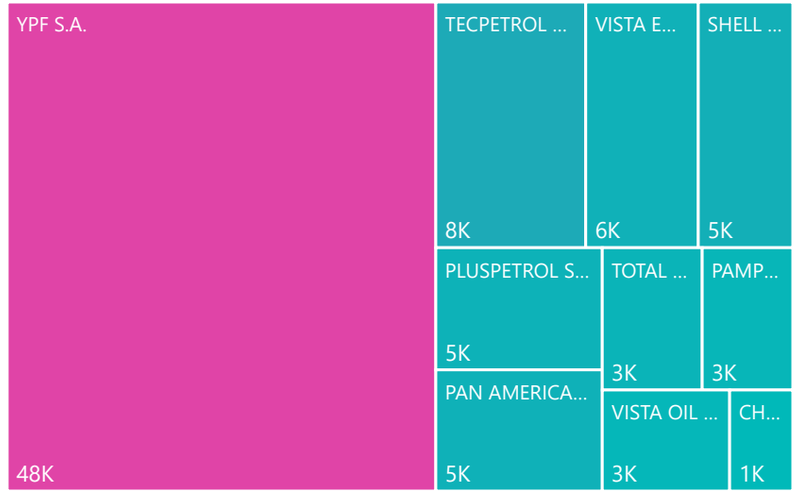

Diego Angeloni - Marzo 2026

ARGENTINA UPSTREAM DASHBOARDS

FRACKING

SELECCIÓN DE PÁGINA

- ACTIVIDAD
- INSUMOS
- PARÁMETROS

INSUMOS

Arena y agua utilizada en Fracking

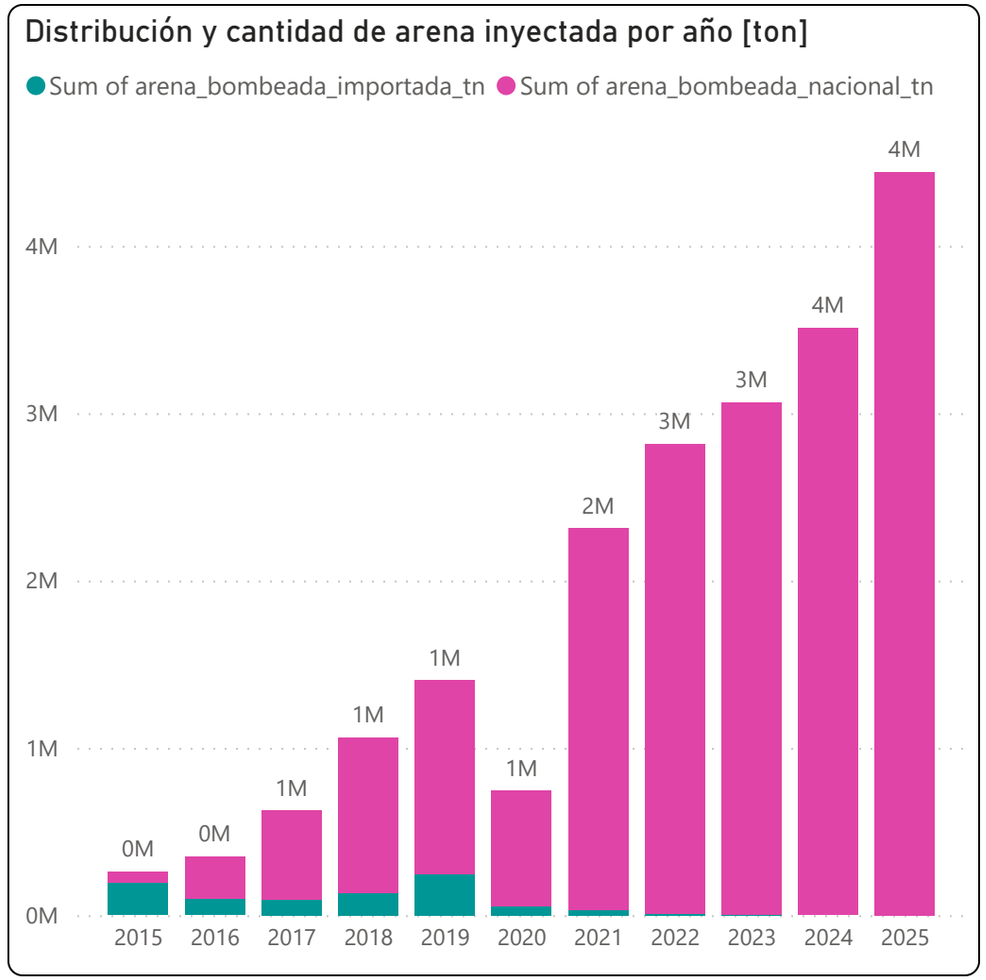

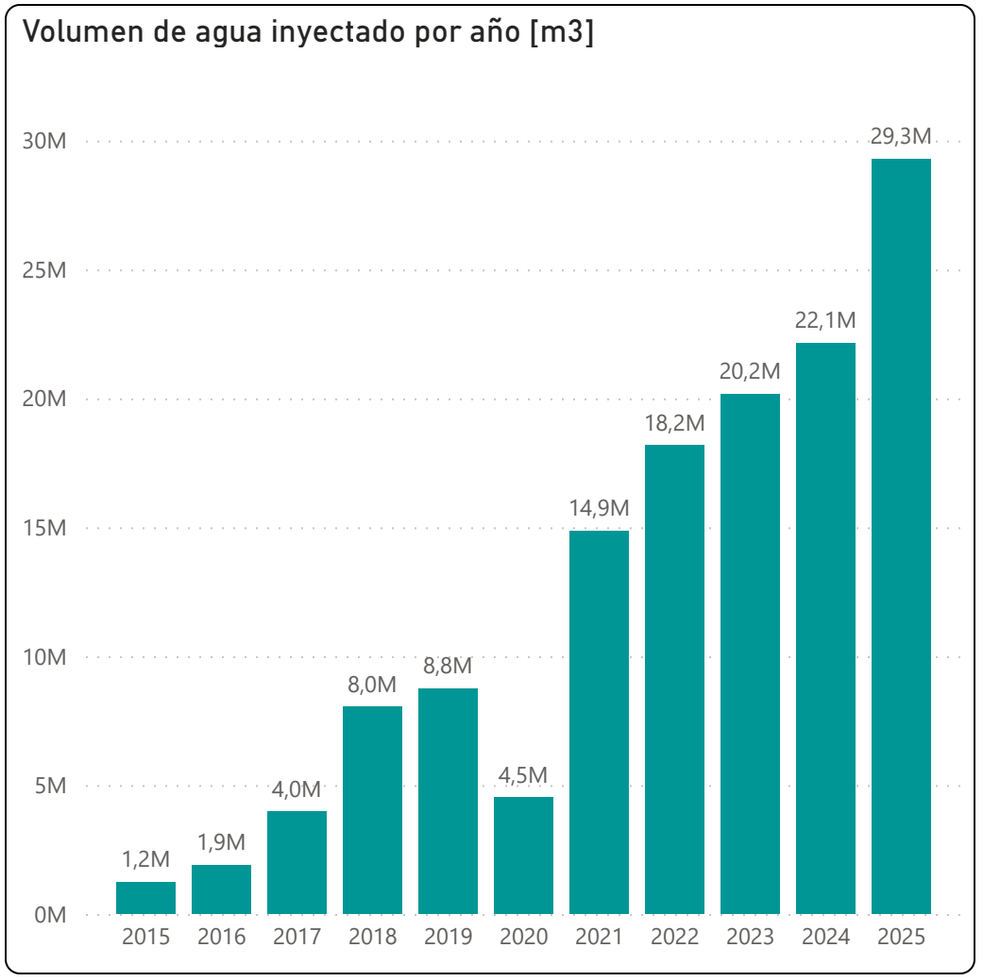

Diego Angeloni - Marzo 2026

ARGENTINA
UPSTREAM
DASHBOARDS

PARÁMETROS

Parámetros operativos de la actividad

FRACKING

Cantidad de fracturas promedio por pozo

33,57

Duración promedio de operación en días

18,56

Promedio de presión máxima alcanzada

11,55K

Potencia promedio de los equipos de bombeo en Hp

29,91K

SELECCIÓN DE PÁGINA

- ACTIVIDAD
- INSUMOS
- PARÁMETROS

Rank	sigla	Year	areapermisoconcesion	longitud_rama_horizontal_m
1	YPF.Nq.SOil-476(h)	2025	LOMA CAMPANA	5114
2	YPF.Nq.LLL-1861(h)	2025	LOMA CAMPANA	4965
3	YPF.Nq.SOil-475(h)	2025	LOMA CAMPANA	4823
4	YPF.Nq.LLL-1862(h)	2025	LOMA CAMPANA	4698
5	YPF.Nq.LACh-416(h)	2025	LA AMARGA CHICA	4551
6	YPF.Nq.LACh-457(h)	2025	LA AMARGA CHICA	4534
7	YPF.Nq.LLL-1863(h)	2025	LOMA CAMPANA	4527
8	YPF.Nq.LLL-1864(h)	2025	LOMA CAMPANA	4507
9	YPF.Nq.LACh-458(h)	2025	LA AMARGA CHICA	4502
10	YPF.Nq.SOil-473(h)	2025	LOMA CAMPANA	4487

Diego Angeloni - Marzo 2026

ARGENTINA
UPSTREAM
DASHBOARDS

PRODUCCIÓN DE PETRÓLEO

SELECCIÓN DE PÁGINA

- Producción nacional
- Áreas y Empresas

PRODUCCIÓN NACIONAL

Distribución de la producción de petróleo a nivel nacional

Periodo

2015 2025

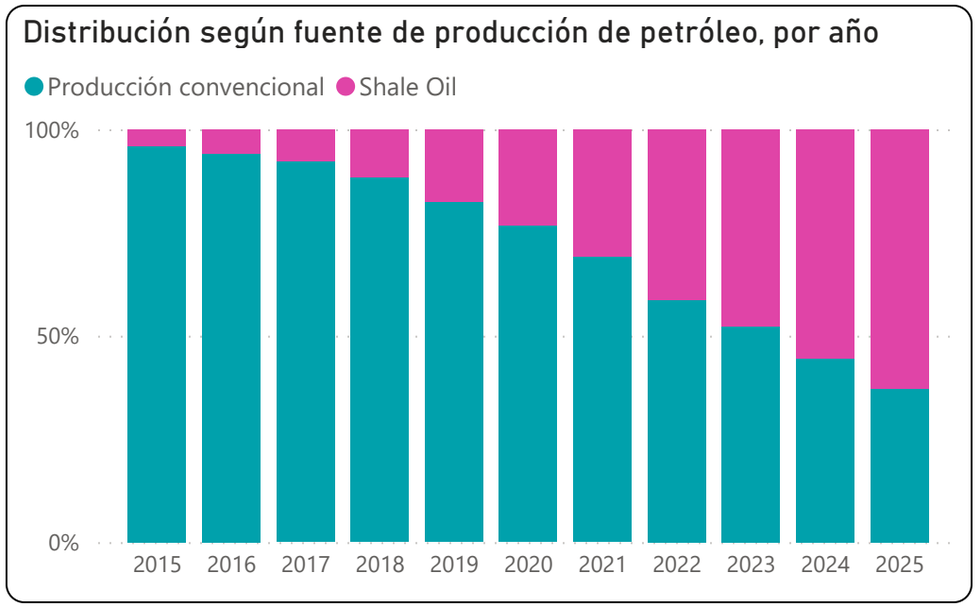

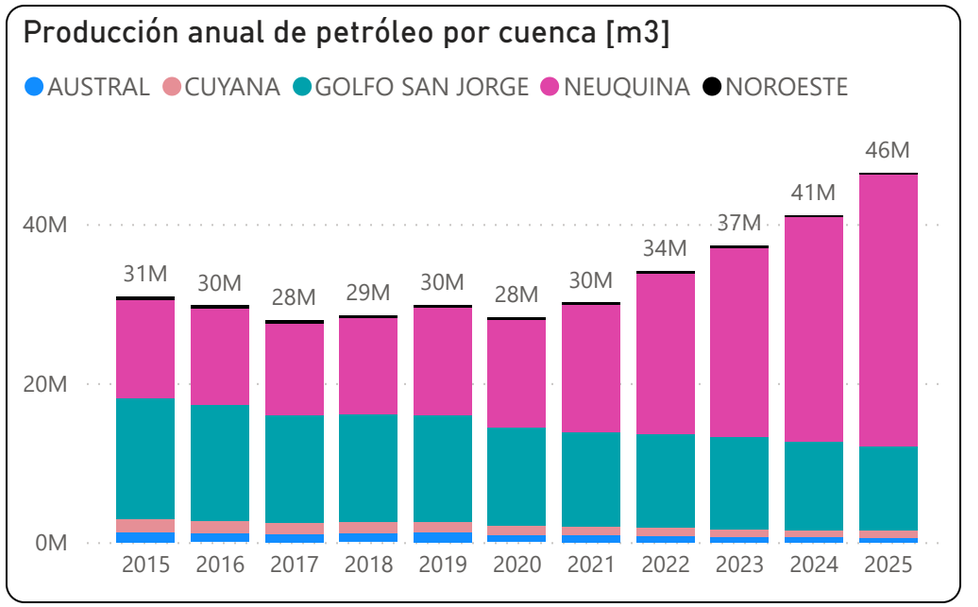

Diego Angeloni - Marzo 2026

ARGENTINA UPSTREAM DASHBOARDS

PRODUCCIÓN DE PETRÓLEO

SELECCIÓN DE PÁGINA

- Producción nacional
- Áreas y Empresas

Diego Angeloni - Marzo 2026

ÁREAS Y EMPRESAS

Producción anual por área y empresa

Área: All

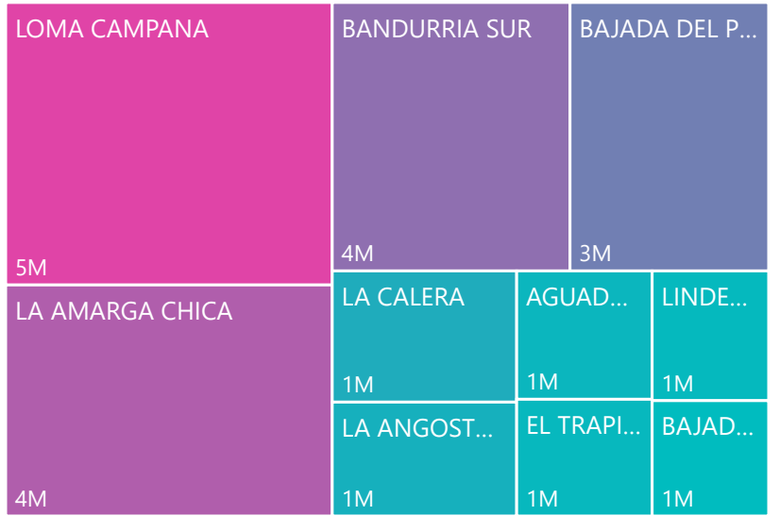

Empresa: All



2025

AUSTRAL | CUYANA | GOLFO SAN JORGE | NEUQUINA | NOROESTE

areapermisoconcesion	empresa	Sum of cantidad_m3
LOMA CAMPANA	YPF S.A.	5138074
LA AMARGA CHICA	YPF S.A.	4201538
BANDURRIA SUR	YPF S.A.	3555127
BAJADA DEL PALO OESTE	VISTA ENERGY ARGENTINA SAU	2969777
LA CALERA	PLUSPETROL S.A.	1347728
LA ANGOSTURA SUR I	YPF S.A.	1169883
AGUADA DEL CHAÑAR	YPF S.A.	968297
EL TRAPIAL ESTE	CHEVRON ARGENTINA S.R.L.	880346
LINDERO ATRAVESADO	PAN AMERICAN ENERGY SL	841848
BAJADA DEL PALO ESTE	VISTA ENERGY ARGENTINA SAU	748537
CRUZ DE LORENA	SHELL ARGENTINA S.A.	709406
BAJO DEL CHOIQUE - LA INVERNADA	PLUSPETROL CUENCA NEUQUINA S.R.L.	681771
CHACHAHUEN SUR	YPF S.A.	672309
MATA MORA NORTE	KILWER S.A.	601489
COIRON AMARGO SUR ESTE	PAN AMERICAN ENERGY SL	582597
RINCON DE ARANDA	PAMPA ENERGIA S.A.	552888
SIERRAS BLANCAS	SHELL ARGENTINA S.A.	509640
JAGÜEL CASA DE PIEDRA	PLUSPETROL S.A.	508484
FORTIN DE PIEDRA	TECPETROL S.A.	472829
COIRON AMARGO SUR OESTE	SHELL ARGENTINA S.A.	440164
Total		**34231624**

ARGENTINA UPSTREAM DASHBOARDS

PRODUCCIÓN DE GAS

SELECCIÓN DE PÁGINA

- Producción nacional
- Áreas y empresas

PRODUCCIÓN NACIONAL

Distribución de la produccion de gas a nivel nacional

Periodo

2015 2025

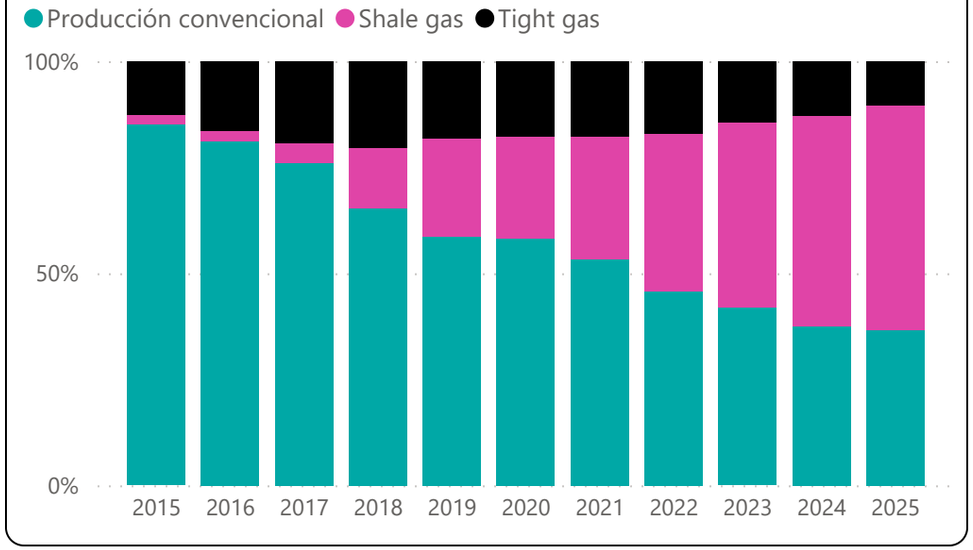

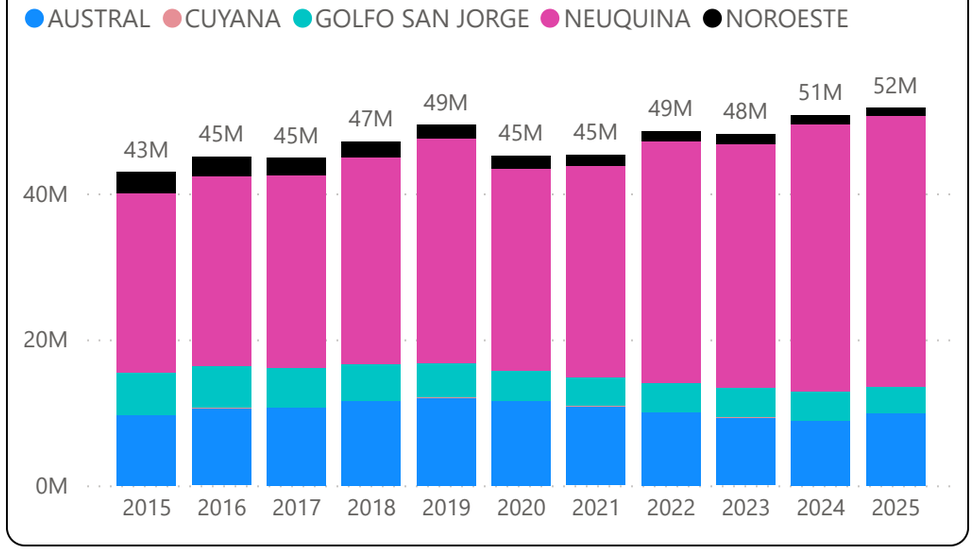

Diego Angeloni - Marzo 2026

ARGENTINA UPSTREAM DASHBOARDS

PRODUCCIÓN DE GAS

SELECCIÓN DE PÁGINA

- Producción nacional
- Áreas y empresas

Diego Angeloni - Marzo 2026

ÁREAS Y EMPRESAS

Producción anual por área y empresa en Mm3

Área: All

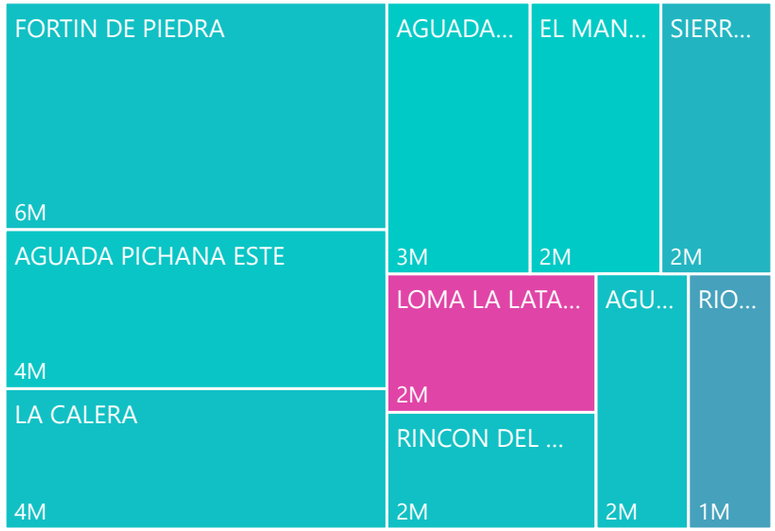

Empresa: All

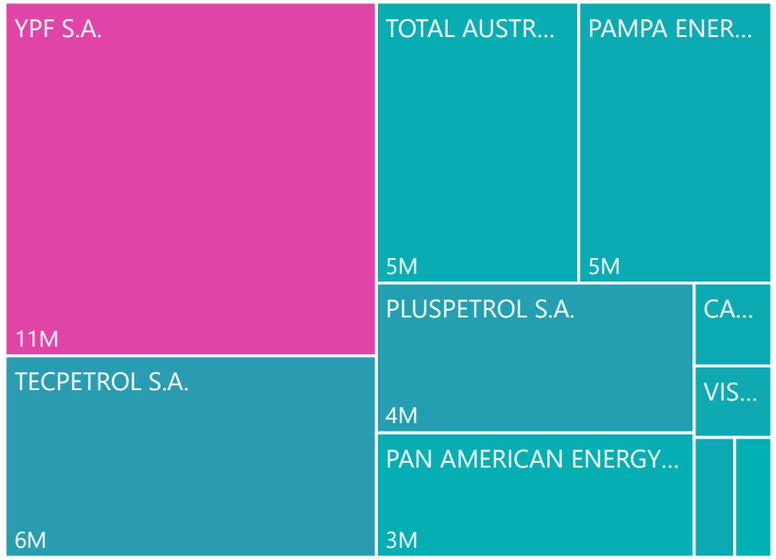

2025

AUSTRAL | CUYANA | GOLFO SAN JORGE | NEUQUINA | NOROESTE

areapermisoconcesion	empresa	Sum of cantidad_mm3
FORTIN DE PIEDRA	TECPETROL S.A.	5867856
AGUADA PICHANA ESTE	TOTAL AUSTRAL S.A.	4101540
LA CALERA	PLUSPETROL S.A.	3618958
AGUADA PICHANA OESTE	PAN AMERICAN ENERGY SL	2625414
EL MANGRULLO	PAMPA ENERGIA S.A.	2402882
SIERRA CHATA	PAMPA ENERGIA S.A.	2033485
LOMA LA LATA - SIERRA BARROSA	YPF S.A.	1957921
RINCON DEL MANGRULLO	YPF S.A.	1648774
AGUADA DE LA ARENA	YPF S.A.	1592136
RIO NEUQUEN	YPF S.A.	1435687
LOMA CAMPANA	YPF S.A.	1104850
BANDURRIA SUR	YPF S.A.	701024
SAN ROQUE	TOTAL AUSTRAL S.A.	555681
EL OREJANO	YPF S.A.	540149
LA AMARGA CHICA	YPF S.A.	501710
LINDERO ATRAVESADO	PAN AMERICAN ENERGY SL	396802
EL TRAPIAL ESTE	CHEVRON ARGENTINA S.R.L.	368744
BAJADA DEL PALO OESTE	VISTA ENERGY ARGENTINA SAU	366436
BAJO DEL CHOIQUE - LA INVERNADA	PLUSPETROL CUENCA NEUQUINA S.R.L.	281593
LA ANGOSTURA SUR I	YPF S.A.	255988